4/11/26

פורום אורבני גינות העיר 14.10.2026 – סיכום

הפורום התקיים בזום.

סדר יום:

- **דובנוב 16**
- **הפלמ"ח 49**
- **אלפסי 9**

- **דובנוב 16 - מס' 101-1389568**

משתתפי הפורום עינו על מסמכי התכנית ולהלן סיכום הערות על התכנית:

- התכנית מציעה בינוי של 8-10 קומות (הפרשי טופוגרפיה) במקום שהבנייה לא עוברת את ה-2-4 קומות.
- התכנית מציעה כניסה לחניון ורמפה במקום הטבעי לשביל מחבר בין דובנוב לרחוב רובין.
- התכנית מציעה חזית רציפה (עבור "גלריה") בקומת הקרקע הפונה לרחוב דובנוב.
- התכנית מציעה בינוי בגובה אחיד ולא בנינים המותאמים לטופופגריה הטבעית.
- התכנית מציעה חזיתות זכוכית לא תואמות את אופי המקום ואת הבניה בירושלים.
- התכנית פוגעת בעצים ווותיקים קיימים בחלקה.
- התכנית מציעה שטח חום לא שמיש (קטן מדי).
- התכנית מציעה הסדרת צומת רובין עם דובנוב וגרץ.

לתכנית יש חוו"ד מהנדס העיר שהיא תואמת את העמדה וההערות של הפורום. הפורום מציע לתמוך בהמלצות מהנדס העיר ולחזק את הנקודות לשיפור והתאמת התכנית לשכונה.

- **הפלמ"ח 49 - מס' 101-1377753**

משתתפי הפורום עינו על מסמכי התכנית ולהלן סיכום הערות על התכנית:

- התכנית מציעה 8 קומות מעל מפלס כניסה הקובעת.
- מדיניות המקום מאפשרת עד 6 קומות, ולכן יש חריגה של 2 קומות מעל המדיניות.
- יש לצמצם גובה הבינוי ו/או לייצר נסיגות.
- לייצר חזית מסחרית עפ"י מדיניות תכנית אב מושבות ולהגדיר שימושים כדי לעודד מסחר מקומי ולחזק עסקים שכונתיים.

- החניון המוצע הוא מפוצל לשניים ולכן דורש 2 כניסות ויציאות. האם יש אפשרות לאחד חניונים עם חיבור תת קרקעי מתחת לכביש?
- גובה גדרות על מבצע קדש - יש להגביל את הגובה עפ"י מדיניות או ככל היותר עד 1.2 מ'.
- התכנית מציעה הרחבת המדרכה לאורך מבצע קדש לרוחב כולל של 2.5 מ'.
- לבקש לבטל גדרות של גינות פרטיות ולהרחיב ולשפר את המדרכה והמרחב הציבורי.
- לבקש ליצר קו בנין תת קרקעי כדי לשמור על עצי אורן על גבולות החלקה.
- תכסית המותר עד 45%. האם יש יותר?
- תקופת הגשת התנגדות עד ה-17/11/26.

לתכנית יש חוו"ד מהנדס העיר שהיא תואמת את העמדה וההערות של הפורום. הפורום מציע לתמוך בהמלצות מהנדס העיר ולחזק את הנקודות לשיפור והתאמת התכנית לשכונה.

- **אלפסי 9 - מס' 1993/0664.03**

1. <u>מדיניות השימור</u>

א. עפ"י תכנית רחביה 9988 המבנה בחלקה 126 ברחוב אלפסי 9 מסומן כמבנה לשימור.



צילום מסך מתוך מסמכי תכנית רחביה 9988

מבנה לשימור עפ"י תוכנית 9988 (כרטסת השימור העירונית מס׳ 3429).

עפ"י סעיף 6.1 לתוכנית רחביה 9988, לא תותר הריסת בניינים לשימור, ולא תותר העתקתם או העתקת חלקים מהם, פירוקם והרכבתם מחדש.

כמו כן, התכנית חורגת מהחלטת וועדת שימור על התכנית שלא לחרוג מזכויות בניה, מקוי בניין ומהוראות התכנית רחביה 9988.

חשוב להזכיר את החלטת וועדת ערער לתכנית ברחל אמנו 17, מבנה אופייני שלא קיבל אישור הריסה אפילו לא של חלק מחזית אחורית.



צילום GIS של החלקה 126 המראה את העצים.

2. <u>התכנית המוצעת</u>

א. המבנה באיזור ב' בו מותר בניה עד 5 קומות מעל מפסל הכניסה הקובעת.

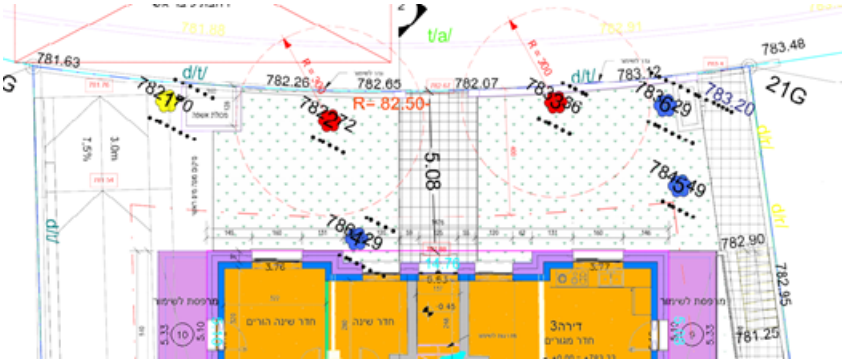
ב. שטח החלקה 713 מ"ר.

ג. בחלקה ישנם עצים בוגרים בעריכות גבוהה בחלק הצפוני וגם בחלק הדרומי של החלקה. כל העצים האלה מהווים חלק מהנוף של שכונת רחביה – שכונת גנים – ומוסיפים לה לאופי וצביון השכונה ההיסטורית.

ד. התכנית מציעה חפירה של כל שטח החלקה.

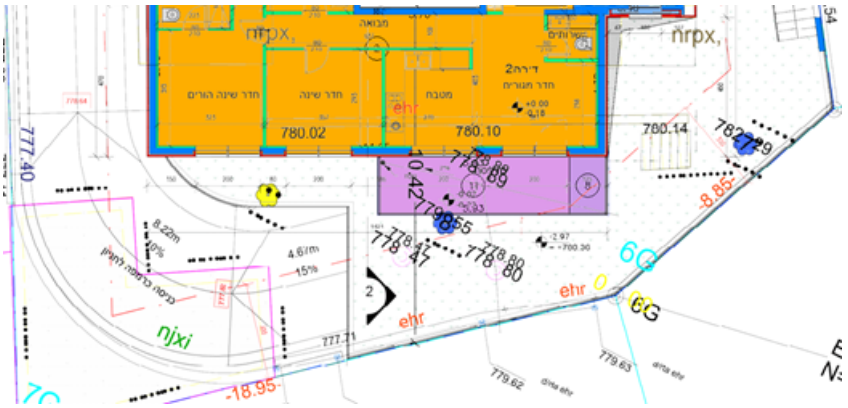
ה. התכנית מציעה כריתה של 5 עצים בחלקה אך לא כוללת סקר עצים ולכן לא ברור מדוע עצים וותיקים מסומנים בכחול ולא בצהוב או אדום.

ו. עפ"י תכנית רחביה 9988 המבנה בחלקה 126 ברחוב אלפסי 9 מסומן כמבנה לשימור.

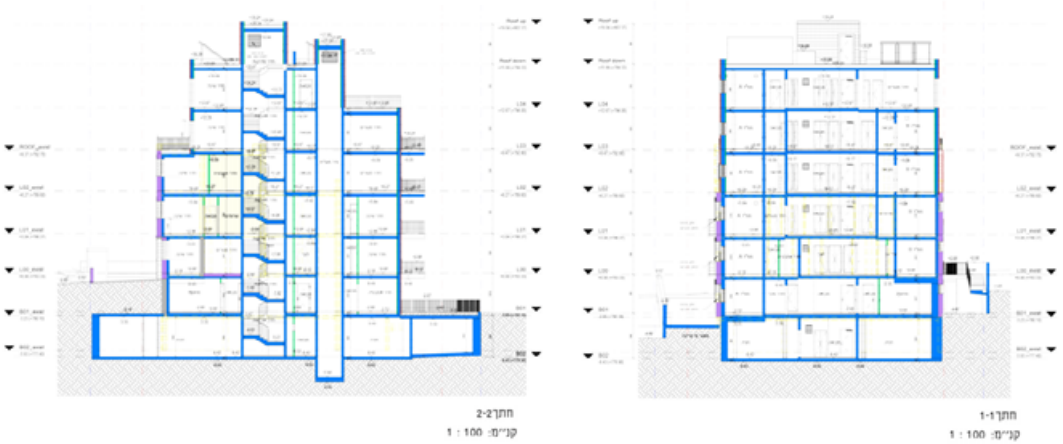


צילום מסך של פרט מתכנית קומת קרקע ממסמכי התכנית

א. כמו כן עצים רבים מסומנים בכחול – ללא גיבוי והסברים של סקר עצים של אגרונום מוסמך.



ב. התכנית מציעה בינוי של 6 קומות מלאות בחתך אחד לפחות ונסיגות בחתך אחר:



חתך 1-1 מתוך מסמכי התכנית *חתך 2-2*

ג. התכנית מציעה בינוי של 6 קומות לפחות בחזית אחת:



מודל תלת מימד מתוך מסמכי התכנית

חשוב לציין כי עפ"י הוראות תכנית רחביה 9988 "במבנים לשימור לפי תכנית לא ניתן להציע חריגה מתכנית מאושרת במסגרת תמ"א בכל מסלול ובכל פרמטר (קומות אחוזי בניה תכסית קווי בניין וכו'). " ולכן, לא ניתן, לא להרוס ולא לחרוג ממדיניות השכונה ההיסטורית ממספר הקומות הנקבע.

3. <u>התנגדות לתכנית המוצעת</u>

לאור החריגות החמורות מתכנית סטטוטורית רחביה 9988, מינהל קהילתי גינות העיר מתנגד לתכנית בנקודות המרכזיות הבאות.

א. חריגה בגובה של 6 קומות + יציאה לגג (= 7 קומות בפועל) במקום 5 קומות עפ"י המדיניות.

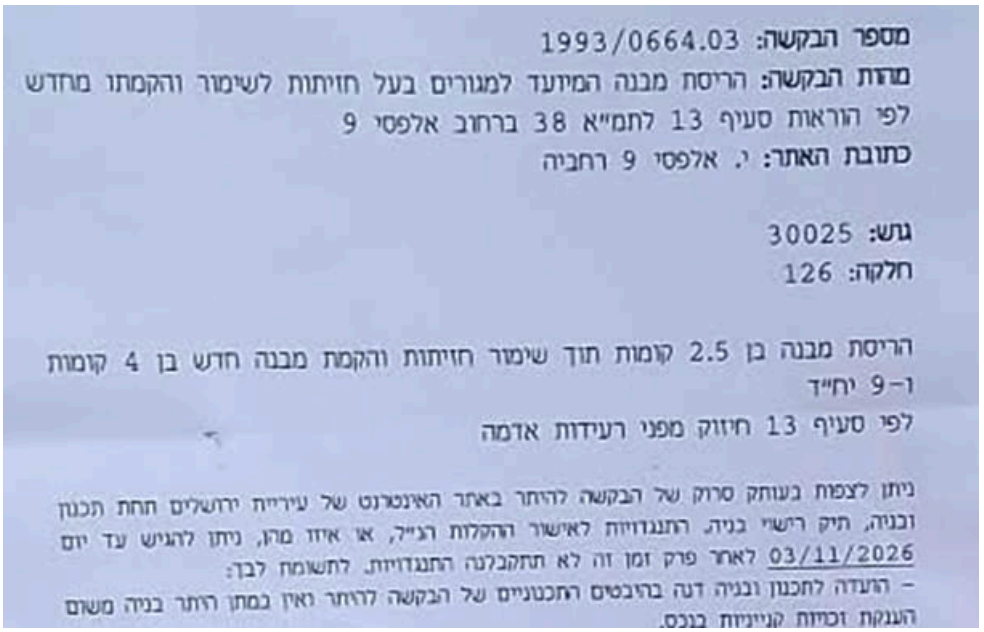
ב. חריגה משימור מבנה המסומן לשימור. חריגה חמורה הפוגעת באופי ואיכות השכונה, יוצרת תקדים להתעלמות מהמלצות וועדת שימור ופגיעה חמורה לאופי ההיסטורי של שכונת רחביה.

ג. כריתה של עצים בוגרים וסימון של עצים בוגרים בעריכות גבוהה בצבע כחול ללא גיבוי בסקר עצים ע"י אגרונום מוסמך. כאשר מדובר בחלקה בלב ההיסטורי של שכונת רחביה – עיר גנים – בלב העיר ההיסטורית של ירושלים.

ד. פרסום לקוי של התכנית לשכים ולסביבה. מפניות ותלונות של תושבים, מתברר כי התכנית פורסמה בשפה לא מדויקת כאשר פירסמה "הריסת מבנה בן 2.5 קומות תוך שימור חזיתות <u>והקמת מבנה חדש בן 4 קומות</u> ו-9 יח"ד." במקום להציג את המצב בפועל, של "מבנה בן 6 קומות".

ה. <u>יש להתיחס למגמה של פרסום מטעה בחומרה, כי הודעות המטעות את הציבור לא מאפשרות לציבור לממש את הזכות החוקית שלו להתנגד לתכנית החורגת ממדיניות השכונה שלהם.</u>

ו. <u>לאור התנהלות מטעה כלפי הציבור, המינהל דורש לבטל את הליך הפירסום ולקיים אותו מחדש ע"י פרסום של הודעות מדויקות.</u>



מספר הבקשה: 1993/0664.03
מהות הבקשה: הריסת מבנה המיועד למגורים בעל חזיתות לשימור והקמתו מחדש לפי הוראות סעיף 13 לתמ"א 38 ברחוב אלפסי 9
כתובת האתר: י. אלפסי 9 רחביה

גוש: 30025
חלקה: 126

הריסת מבנה בן 2.5 קומות תוך שימור חזיתות והקמת מבנה חדש בן 4 קומות ו-9 יח"ד
לפי סעיף 13 חיזוק מפני רעידות אדמה

ניתן לצפות בעותק סרוק של הבקשה להיתר באתר האינטרנט של עיריית ירושלים תחת תכנון ובניה, תיק רישוי בניה. התנגדויות לאישור ההקלות הנ"ל, או איזו מהן, ניתן להגיש עד יום 03/11/2026 לאחר פרק זמן זה לא תתקבלנה התנגדויות. לתשומת לבך:
- הועדה לתכנון ובניה דנה בהיבטים התכנוניים של הבקשה להיתר ואין במתן היתר בניה משום הענקת זכויות קנייניות בנכס.



עיריית ירושלים

הוועדה המקומית לתכנון ולבניה
הודעה לפי סעיף 149 לחוק התכנון והבניה

ניתנת בזה הודעה בהתאם לסעיף 149 לחוק התכנון והבניה תשכ"ה 1965, כי הוגשה לוועדה בקשה להיתר ע"י: **דניאל וולפסון**

מספר הבקשה: 1993/0664.03
מהות הבקשה: הריסת מבנה המיועד למגורים בעל חזיתות לשימור והקמתו מחדש לפי הוראות סעיף 13 לתמ"א 38 ברחוב אלפסי 9
כתובת האתר: י. אלפסי 9 רחביה

גוש: 30025
חלקה: 126

הריסת מבנה בן 2.5 קומות תוך שימור חזיתות והקמת מבנה חדש בן 4 קומות ו-9 יח"ד
לפי סעיף 13 חיזוק מפני רעידות אדמה

ניתן לצפות בעותק סרוק של הבקשה להיתר באתר האינטרנט של עיריית ירושלים תחת תכנון ובניה, תיק רישוי בניה. התנגדויות לאישור ההקלות הנ"ל, או איזו מהן, ניתן להגיש עד יום 03/11/2026 לאחר פרק זמן זה לא תתקבלנה התנגדויות. לתשומת לבך:
- הועדה לתכנון ובניה דנה בהיבטים התכנוניים של הבקשה להיתר ואין במתן היתר בניה משום הענקת זכויות קנייניות בנכס.
- מתן היתר הבניה אינו מאשרר את בעלות מתבקשים כלפי הדיירים או כלפי בעלי זכות אחרת לפי דין.
- אם לא ברורה לך משמעות המכתב ומסמכיו עליך לפנות לאיש מקצוע מתאים.
- כאם תוגש התנגדות, תדון בה הועדה המקומית. עמדת הפטיבות תהיה באם לקיים את הדיון במעמד הנדרשים או ללא נוכחותם.
הבאים לפתוח להגשת התנגדות נמצא באתר האינטרנט של עיריית ירושלים תחת יחכנון ובניה, כתב התנגדות לבקשה להיתרי.

יו"ר הועדה המקומית לתכנון ובניה
מר אליעזר ראכברגר

אגף רישוי בניה, קריית הממשלה, כיכר ספרא 1 טלפון: 02-6295474
שעות פעולה טלפוני ימים א, ה בין השעות 8:30-12:30

לפרטים נוספים על נושאים אורבניים בגינות העיר יש לעיין ב**לוח מודעות על נושאים אורבניים:** LINK
עידכונים אורבניים בגינות העיר:

אוגוסט 2026: PDF
מרץ 2026: PDF
דצמבר 2025: PDF
יוני 2025: PDF
דצמבר 2024: PDF וקישור
אוגוסט 2024: PDF וקישור
מאי 2024: PDF וקישור
ינואר 2024: PDF
מרץ 2023: https://app.activetrail.com/S/3iaiztzj3wdx.htm
נובמבר 2022: https://app.activetrail.com/S/3iaiztzdxajt.htm
יולי 2022: https://app.activetrail.com/S/3iaiztzeatdz.htm
מאי 2022: https://app.activetrail.com/S/3iaiztz3wdja.htm
אפריל 2022: https://katzr.net/508aac

הפורום הבא מתקיים כמתוכנן ב-4/11/26 בשעה 20:30 בזום.